MIEJSCOWY PLAN ZAGOSPODAROWANIA PRZESTRZENNEG

ZAŁACZNIK NR 1 DO UCHWAŁY NR XIV/110/25 Z DNIA 2 LIPCA 2025 R.

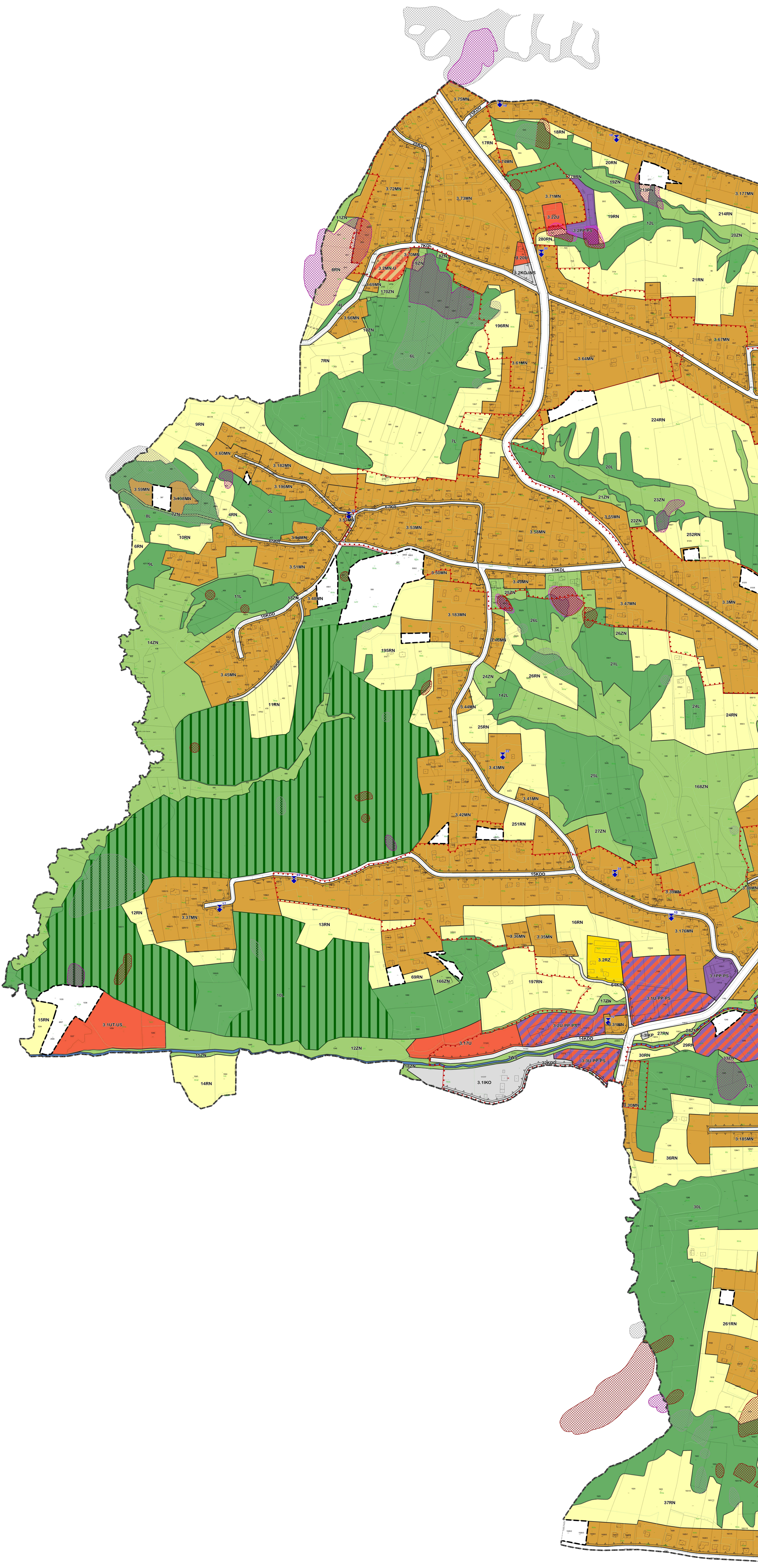

0 100 200 m

SKALA 1:2000

Układ współrzędnych: PL-2000 strefa 7
źródło danych: Starostwo Powiatowe w Myślenicach-
Powiatowy Osrodek Dokumentacji Geodezyjnej i Kartograficznej
Licencja z dnia 11.03.2024 r.

LEGENDA

OBOWIĄZUJĄCE USTALENIA PLANU

▬ ▬ ▬	GRANICE OBSZARU OBJĘTEGO PLANEM
───	LINIE ROZGRANICZAJĄCE TERENY O RÓŻNYM PRZEZNACZENIU LUB RÓŻNYCH ZASADACH ZAGOSPODAROWANIA
▽ ▽	NIEPRZEKRACZALNE LINIE ZABUDOWY OD DRÓG
▼ ▼ ▼	GRANICA STREFY POTENCJALNEGO PONADNORMATYWNEGO ODDZIAŁYWANIA TERENÓW KOMUNIKACJI
MN	TERENY ZABUDOWY MIESZKANIOWEJ JEDNORODZINNEJ
MN-U	TERENY ZABUDOWY MIESZKANIOWEJ JEDNORODZINNEJ LUB USŁUG
U	TERENY USŁUG
UE	TERENY USŁUG EDUKACJI
UR	TERENY USŁUG KULTU RELIGIJNEGO
UB-UA	TERENY USŁUG BEZPIECZEŃSTWA I PORZADKU PUBLICZNEGO LUB USŁUG BIUROWYCH I ADMINISTRACJI
UT-US	TERENY USŁUG TURYSTYKI LUB USŁUG SPORTU I REKREACJI
UT-US-ZN	TERENY USŁUG TURYSTYKI LUB USŁUG SPORTU I REKREACJI LUB ZIELENI NATURALNEJ
US	TERENY USŁUG SPORTU I REKREACJI
U-PP-PS	TERENY USŁUG LUB PRODUKCJI PRZEMYSŁOWEJ LUB SKŁADÓW I MAGAZYNÓW
PP-PS	TERENY PRODUKCJI PRZEMYSŁOWEJ LUB SKŁADÓW I MAGAZYNÓW
KDG	TEREN DROGI GŁÓWNEJ
KDZ	TERENY DRÓG ZBIORCZYCH
KDL	TERENY DRÓG LOKALNYCH
KDD	TERENY DRÓG DOJAZDOWYCH
KR	TERENY KOMUNIKACJI DROGOWEJ WEWNĘTRZNEJ
KO	TERENY OBSŁUGI KOMUNIKACJI
KO-INS	TERENY OBSŁUGI KOMUNIKACJI LUB STACJI PALIW PŁYNNYCH
IG	TEREN GAZOWNICTWA
IW	TERENY WODOCIĄGÓW
IKP	TERENY POMPOWNI ŚCIEKÓW
IKO	TEREN OCZYSZCZALNI ŚCIEKÓW
RN	TERENY ROLNICTWA Z ZAKAZEM ZABUDOWY
RZ	TERENY ZABUDOWY ZWIAZANEJ Z ROLNICTWEM
RA	TEREN AKWAKULTURY I OBSŁUGI RYBACTWA
WS	TERENY WÓD POWIERZCHNIOWYCH ŚRÓDLĄDOWYCH
L	TERENY LASÓW
ZN	TERENY ZIELENI NATURALNEJ
ZP	TERENY ZIELENI URZĄDZONEJ
C	TERENY CMENTARZY

ELEMENTY WYNIKAJĄCE Z OBOWIĄZUJACYCH PRZEPISÓW I DECYZJI ODRĘBNYCH

⌒	GRANICA STREFY OCHRONY POŚREDNIEJ DLA UJĘCIA WODY POWIERZCHNIOWEJ Z RZEKI SKAWINKI
▼ ▼	GRANICA STREFY OCHRONY POŚREDNIEJ I RZĘDU UJĘCIA WODY POWIERZCHNIOWEJ ZE ZBIORNIKA DOBCZYCKIEGO
◆ ◆	GRANICA STREFY OCHRONY POŚREDNIEJ II RZĘDU UJECIA WODY POWIERZCHNIOWEJ ZE ZBIORNIKA DOBCZYCKIEGO
▼ ▼ ▼	GRANICE PROJEKTOWANEGO ZBIORNIKA RETENCYJNEGO "PASTERNIK"
‐ ‐ ‐ ‐	STREFY SANITARNE 50 m OD CMENTARZY
‐ ‐ ‐ ‐	STREFY SANITARNE 150 m OD CMENTARZY
▩	OBSZAR WYSTĘPOWANIA OSUWISK AKTYWNYCH CIĄGLE (wg SOPO)
▩	OBSZAR WYSTĘPOWANIA OSUWISK AKTYWNYCH OKRESOWO (wg SOPO)
▩	OBSZAR WYSTĘPOWANIA OSUWISK NIEAKTYWNYCH LUB TERENÓW POTENCJALNIE NARAŻONYCH NA WYSTĘPOWANIE RUCHÓW MASOWYCH (wg SOPO)
▩	OBSZAR OSUWISK AKTYWNYCH NA PODSTAWIE UCHWAŁY NR XLVIII/331/10 RADY GMINY SIEPRAW Z DNIA 10.11.2010 R.
◆	POMNIKI PRZYRODY
▌ ▌	LASY OCHRONNE
106-57/7	STANOWISKA ARCHEOLOGICZNE
🏛	OBIEKTY WPISANE DO REJESTRU ZABYTKÓW
▬ ▬ ▬	GRANICE ZESPOŁU DWORSKIEGO ORAZ OTOCZENIA KOŚCIOŁA WG WPISU DO REJESTRU ZABYTKÓW
15	OBIEKTY UJĘTE W GMINNEJ EWIDENCJI ZABYTKÓW
‐•‐•‐	GRANICE OBSZARU AGLOMERACJI SIEPRAW
‐•‐•‐	GRANICE OBSZARU AGLOMERACJI DOBCZYCE CENTRUM

ELEMENTY INFORMACYJNE, NIE STANOWIĄCE USTALEŃ PLANU

───	CIĄGI WIDOKOWE
◇	PUNKTY WIDOKOWE
═══	RUROCIĄGI TRANZYTOWE Z ZUW RABA O ŚREDNICACH ø 1000 mm i ø 1400 mm WRAZ ZE STREFĄ TECHNICZNĄ
═══	LINIE ELEKTROENERGETYCZNE WYSOKIEGO NAPIĘCIA 110kV WRAZ ZE STREFĄ TECHNICZNĄ
═══	GAZOCIĄGI WYSOKIEGO CIŚNIENIA DN 200, DN300 i DN 500 WRAZ ZE STREFĄ KONTROLOWANĄ
▬ ▬	GRANICE MIEJSCOWOŚCI
‐ ‐ ‐	GRANICA GMINY

ARKUSZ 1

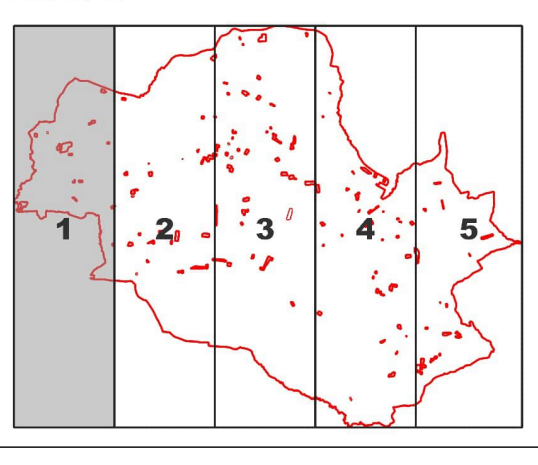

EGO GMINY SIEPRAW W GRANICACH ADMINISTRACYJNYCH WSI: SIEPRAW, ZAK

ARKUSZ 2

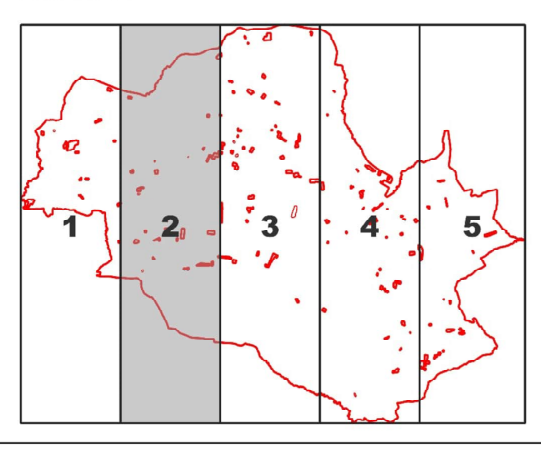

KLICZYN, CZECHÓWKA I ŁYCZANKA - OBSZAR A

ARKUSZ 3

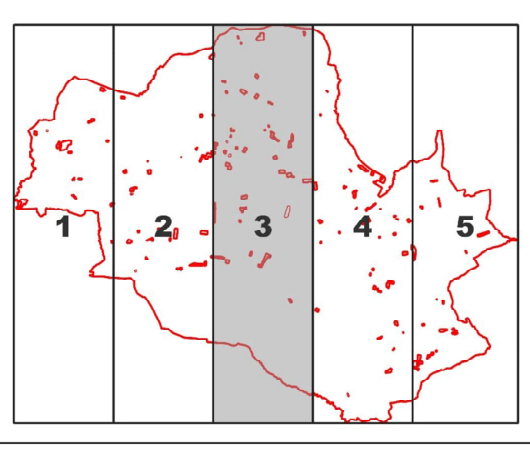

124ZN
ARKUSZ 4
1
2
3
4
5

ZMIANA STUDIUM UWARUNKOWAŃ I KIERUNKÓW ZAGOSPODAROWANIA PRZESTRZENNEGO GMINY SIEPRAW

KIERUNKI ZAGOSPODAROWANIA PRZESTRZENNEGO

ZAŁĄCZNIK NR 2 DO UCHWAŁY RADY GMINY NR XLVIII/324/2010 Z DNIA 10 LISTOPADA 2010 R.

SKALA 1:10 000

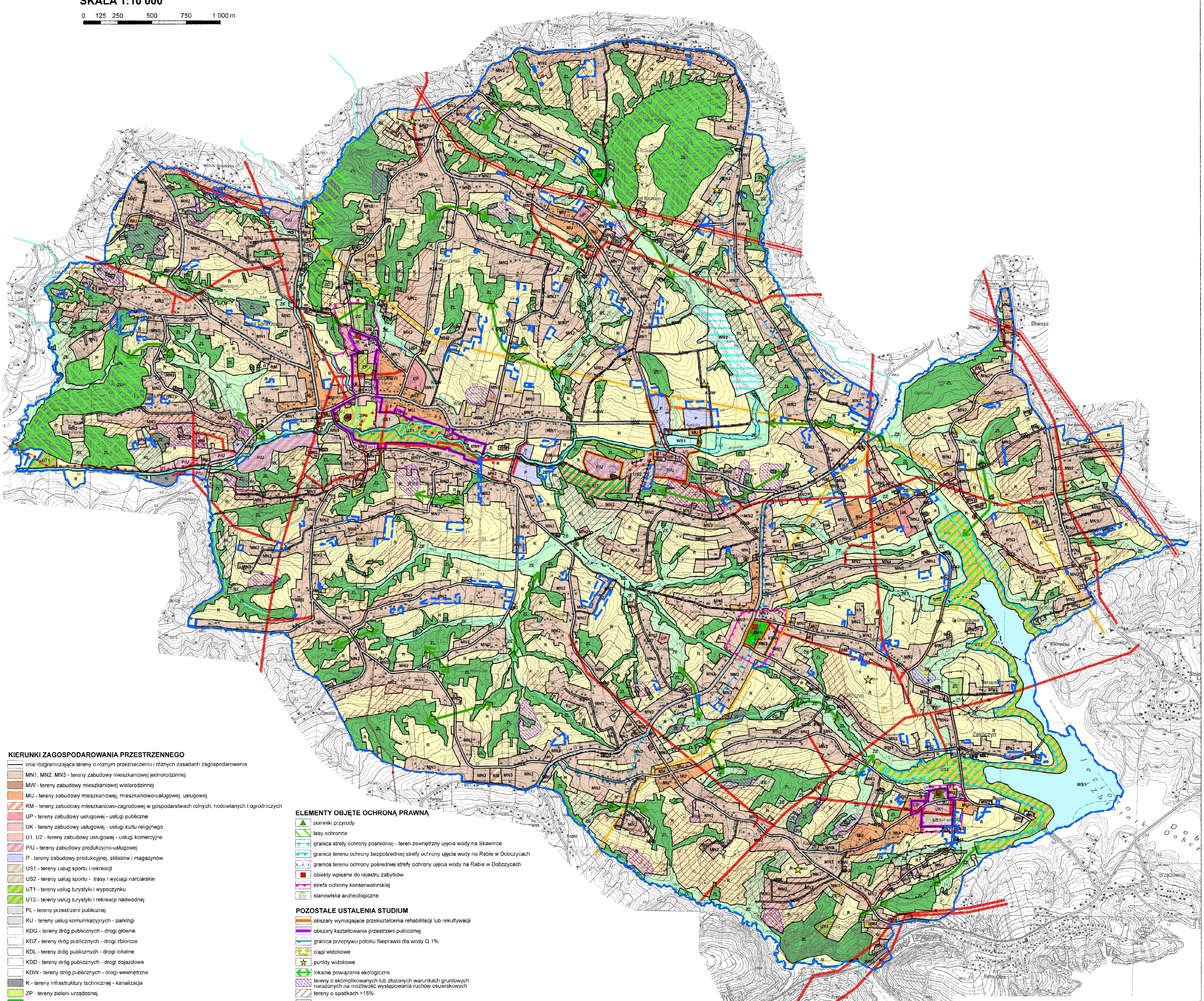

KIERUNKI ZAGOSPODAROWANIA PRZESTRZENNEGO

- linie rozgraniczające tereny o różnym przeznaczeniu i różnych zasadach zagospodarowania
- MN1, MN2, MN3 - tereny zabudowy mieszkaniowej jednorodzinnej
- MW - tereny zabudowy mieszkaniowej wielorodzinnej
- MU - tereny zabudowy mieszkaniowej, mieszkaniowo-usługowej, usługowej
- RM - tereny zabudowy mieszkaniowo-zagrodowej w gospodarstwach rolnych, hodowlanych i ogrodniczych
- UP - tereny zabudowy usługowej - usługi publiczne
- UK - tereny zabudowy usługowej - usługi kultu religijnego
- U1, U2 - tereny zabudowy usługowej - usługi komercyjne
- P/U - tereny zabudowy produkcyjno-usługowej
- P - tereny zabudowy produkcyjnej, składów i magazynów
- US1 - tereny usług sportu i rekreacji
- US2 - tereny usług sportu - trasy i wyciągi narciarskie
- UT1 - tereny usług turystyki i wypoczynku
- UT2 - tereny usług turystyki i rekreacji nadwodnej
- PL - tereny przestrzeni publicznej
- KU - tereny usług komunikacyjnych - parkingi
- KDG - tereny dróg publicznych - drogi główne
- KDZ - tereny dróg publicznych - drogi zbiorcze
- KDL - tereny dróg publicznych - drogi lokalne
- KDD - tereny dróg publicznych - drogi dojazdowe
- KDW - tereny dróg publicznych - drogi wewnętrzne
- K - tereny infrastruktury technicznej - kanalizacja
- ZP - tereny zieleni urządzonej
- ZN - tereny zieleni objęte formami ochrony wraz z obiektami zabytkowymi
- ZC - tereny cmentarzy
- ZE - tereny zieleni nieurządzonej i obudowy biologicznej cieków wodnych
- ZL - tereny lasów
- R - tereny rolne - bez prawa zabudowy
- RL - tereny rolne z możliwością zalesień
- RL/UT - tereny rolne z możliwością zalesień i wykorzystaniem dla potrzeb turystyki narciarskiej i rowerowej
- WS1 - tereny wód śródlądowych
- WS2 - tereny wód śródlądowych - projektowany zbiornik retencyjny "Pasternik"

ELEMENTY OBJĘTE OCHRONĄ PRAWNĄ

- ▲ pomniki przyrody
- lasy ochronne
- granica strefy ochrony pośredniej - teren zewnętrzny ujęcia wody na Skawince
- granica terenu ochrony bezpośredniej strefy ochrony ujęcia wody na Rabie w Dobczycach
- granica terenu ochrony pośredniej strefy ochrony ujęcia wody na Rabie w Dobczycach
- 🟥 obiekty wpisane do rejestru zabytków
- strefa ochrony konserwatorskiej
- stanowiska archeologiczne

POZOSTAŁE USTALENIA STUDIUM

- obszary wymagające przekształcenia rehabilitacji lub rekultywacji
- obszary kształtowania przestrzeni publicznej
- granica przepływu potoku Sieprawki dla wody Q 1%
- ciągi widokowe
- ☆ punkty widokowe
- ↔ lokalne powiązania ekologiczne
- tereny o skomplikowanych lub złożonych warunkach gruntowych narażonych na możliwość występowania ruchów osuwiskowych
- tereny o spadkach >15%
- tereny, które wymagać mogą sporządzenia wniosku rolnego
- linie energetyczne 110 kV wraz ze strefą techniczną
- linie energetyczne 15 kV wraz ze strefą techniczną
- gazociąg wyskiego ciśnienia wraz ze strefą bezpieczeństwa
- magistrala wodociągowa
- ● istniejące pompownie ścieków
- ◉ projektowane pompownie ścieków
- strefy ochrony sanitarnej cmentarzy 50m i 150m
- • • scieżki i trasy pieszo-rowerowe

INNE OZNACZENIA

- wyciągi narciarskie
- granica gminy - granica opracowania
- granice wsi

	ZMIANA STUDIUM UWARUNKOWAŃ I KIERUNKÓW ZAGOSPODAROWANIA PRZESTRZENNEGO GMINY SIEPRAW		
	KIERUNKI ZAGOSPODAROWANIA PRZESTRZENNEGO		SKALA 1:10 000 DATA 10.11.2010
	Zespół Autorski	Imię i Nazwisko	
GIS	Główny Projektant	mgr Jerzy Baścik członek Okręgowej Izby Urbanistów nr KT-351	
	Zespół Projektowy	mgr Kinga Kuczyńska mgr inż. Łukasz Kotuła mgr inż. Teresa Mądry mgr Ireneusz Wójcik	
	Opracowanie Graficzne	mgr Ireneusz Wójcik mgr Jakub Biegun	

1.65MN
118ZN
1.MU
1.MU
1.MU

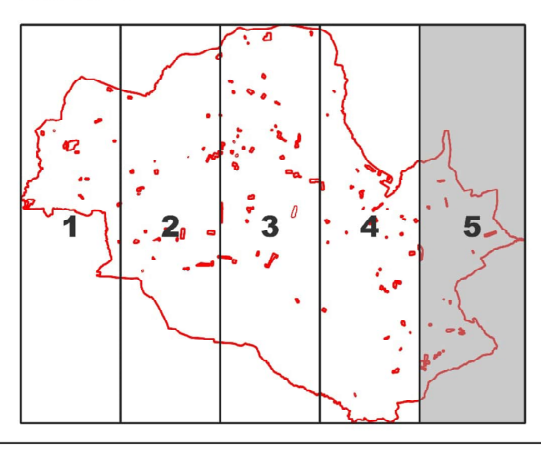ARKUSZ 5